2. 양산악취 수치모델 변수 격자점 지정에 관한 사항

한국형 수치예보모델 단일(지상)면 자료(g576_v091_glob_sfc.*.nc)

변수번호	변수명	설명	단위	층(level)	비고
0	lons	longitude(longitude)	degree_east	-	제공안함
1	lats	latitude(latitude)	degree_north	-	
2	levs	air_pressure(pressure levels)	hPa	-	
3	ilevs	atmosphere_hybrid_sigma_pressure_coordinate(hybrid coefficient at interface)			
4	height_2m	height(2m height)	m	-	
5	height_10m	height(10m height)	m	-	
6	height_80m	height(80m height)	m	-	
7	height_100m	height(100m height)	m	-	
8	soil_levs	depth(soil layer mid-point depth)	m	-	
9	soil_levs_bnds		-	-	
10	time	time(day)	-	-	
11	time_ini				
12	time_bnds				
13	time_ini_bnds				
14	slmsk	land_binary_mask(0:sea, 1:land, 2:sice mask)	-		
15	seaice	sea_ice_area_fraction(seaice area fraction)	1	-	
16	topo	surface_altitude(topography)	m	-	
17	ps	surface_air_pressure(surface pressure)	Pa	-	
18	sst	sea_surface_temperature(sea surface temperature)	K	-	
19	tsfc	surface_temperature(surface temperature)	K	-	
20	u10m	eastward_wind(10m zonal wind)	m/s	1(height_10m)	
21	v10m	northward_wind(10m meridional wind)	m/s	1(height_10m)	
22	u80m	eastward_wind(80m zonal wind)	m/s	1(height_80m)	
23	v80m	northward_wind(80m meridional wind)	m/s	1(height_80m)	
24	gust	wind_speed_of_gust(max wind speed)	m/s	1(height_10m)	
25	t2m	air_temperature(2m temperature)	K	1(height_2m)	
26	rh2m	relative_humidity(2m relative humidity)	%	1(height_2m)	
27	rh2m_liq	(2m relative humidity with respect to water)	%	-	
28	q2m	specific_humidity(2m specific_humidity)	kg/kg	1(height_2m)	
29	qv2m	mixing_ratio(2m mixing_ratio)	kg/kg	1(height_2m)	

양산 인근 AWS 관측소 관측자료(예시 : 양산상북, 84m)

[매분관측자료] 양산상북 905 (84m) / 2026.02.26.10:50 / 경상남도 양산시 상북면

시:분	강수	강수15M	강수60M	강수3H	강수6H	강수12H	일강수	기온℃	풍향1M		풍속1M(m/s)	풍향10M		풍속10M(m/s)	습도%	해면기압hPa
10:50	○	0	0	0	0	0	0	9.8	35.9	NE	2.8	48.0	NE	2.1	60	1021.1
10:49	○	0	0	0	0	0	0	9.8	294.5	WNW	2.6	56.8	ENE	2.0	62	1021.1
10:48	○	0	0	0	0	0	0	9.9	68.6	ENE	2.3	60.4	ENE	2.0	61	1021.1
10:47	○	0	0	0	0	0	0	9.9	53.4	NE	2.3	44.5	NE	1.8	62	1021.2
10:46	○	0	0	0	0	0	0	9.9	330.9	NNW	1.9	26.4	NNE	1.6	62	1021.1
10:45	○	0	0	0	0	0	0	9.8	306.8	NW	1.6	59.8	ENE	1.6	61	1021.1

KIM 8km 수치예보 요소

변수명	의미	단위
topo	해발고도	m
ps	해면기압	pa
u10m	10m 높이 동서성분 바람	m/s
v10m	10m 높이 남북성분 바람	m/s
u80m	80m 높이 동서성분 바람	m/s
u80m	80m 높이 남북성분 바람	m/s
t2m	2m 높이 기온	k
rh2m	3m 높이 상대습도	%

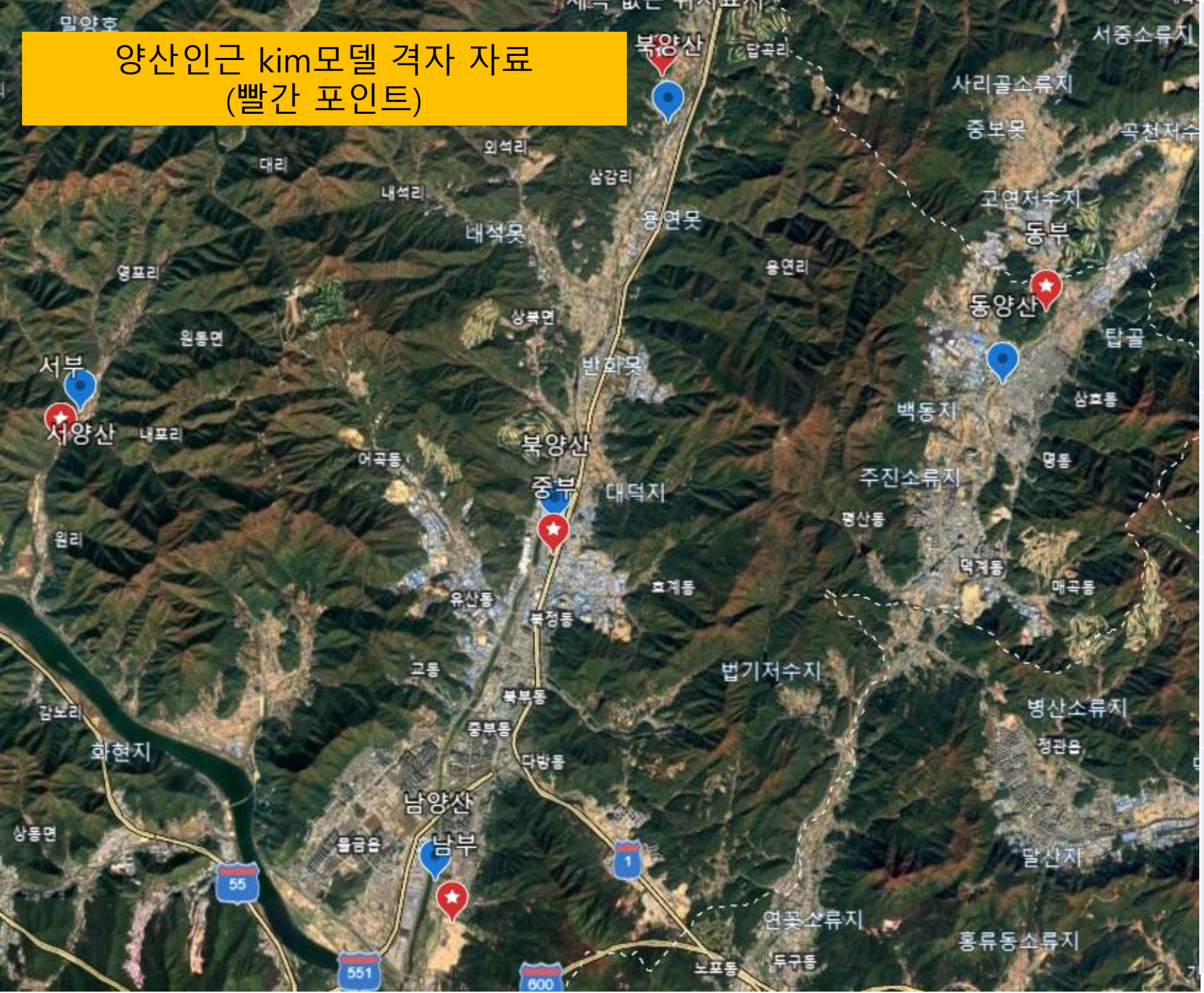

지점명	모델 해발고도(m)	모델위도 (DMS)	모델경도 (DMS)
중부	22	35°22′30.0″	129°3′0.0″
동부	110	35°25′30.0″	129°10′30.0″
서부	40	35°23′60.0″	128°55′30.0″
남부	5	35°17′60.0″	129°1′30.0″
북부	80	35°28′30.0″	129°4′30.0″

지점명	모델 해발고도(m)	모델위도 (DMS)	모델경도 (DMS)
중부	22	35°22′30.0″	129°3′0.0″
동부	110	35°25′30.0″	129°10′30.0″
서부	40	35°23′60.0″	128°55′30.0″
남부	5	35°17′60.0″	129°1′30.0″
북부	80	35°28′30.0″	129°4′30.0″

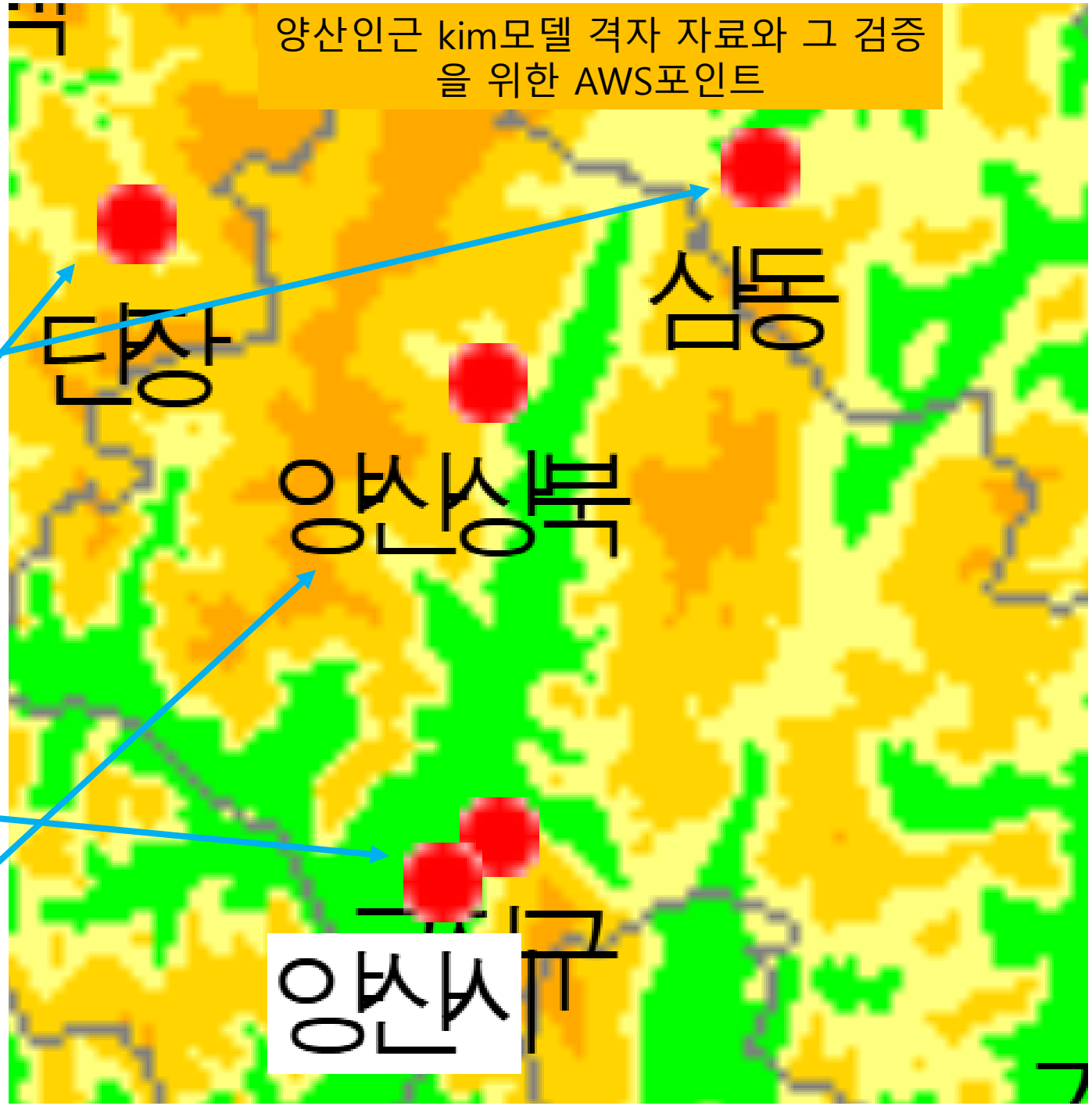

양산인근 AWS 메타정보

지점	시작일	지점명	지점주소	위도	경도	노장해발고도(m)
854	2023-10-26	삼동	울산광역시 울주군 삼동면 금곡리	35.4953	129.1336	166.92
905	2021-07-24	양산상북	경상남도 양산시 상북면	35.4414	129.0429	83.57
922	2022-10-13	단장	경상남도 밀양시 단장면 고례리	35.4865	128.9291	138.03
257	2008-12-26	양산시	경상남도 양산시 동면 금산리	35.3074	129.0201	6.29

지점명	모델 해발고도(m)	모델위도 (DMS)	모델경도 (DMS)
중부	22	35°22′30.0″	129°3′0.0″
동부(삼동)	110	35°25′30.0″	129°10′30.0″
서부(단장)	40	35°23′60.0″	128°55′30.0″
남부(양산시)	5	35°17′60.0″	129°1′30.0″
북부(양산상북)	80	35°28′30.0″	129°4′30.0″

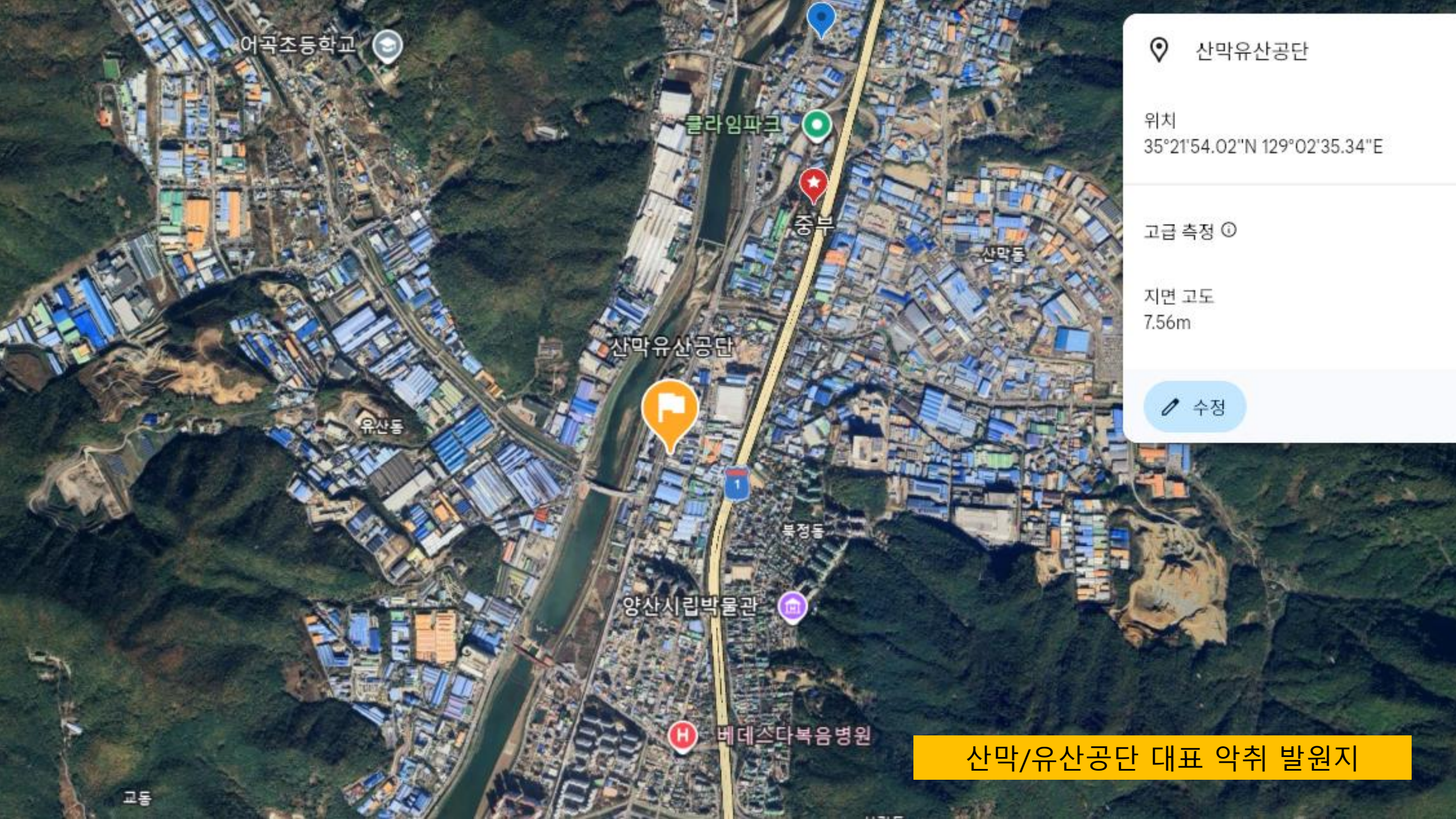

산막/유산공단 대표 악취 발원지

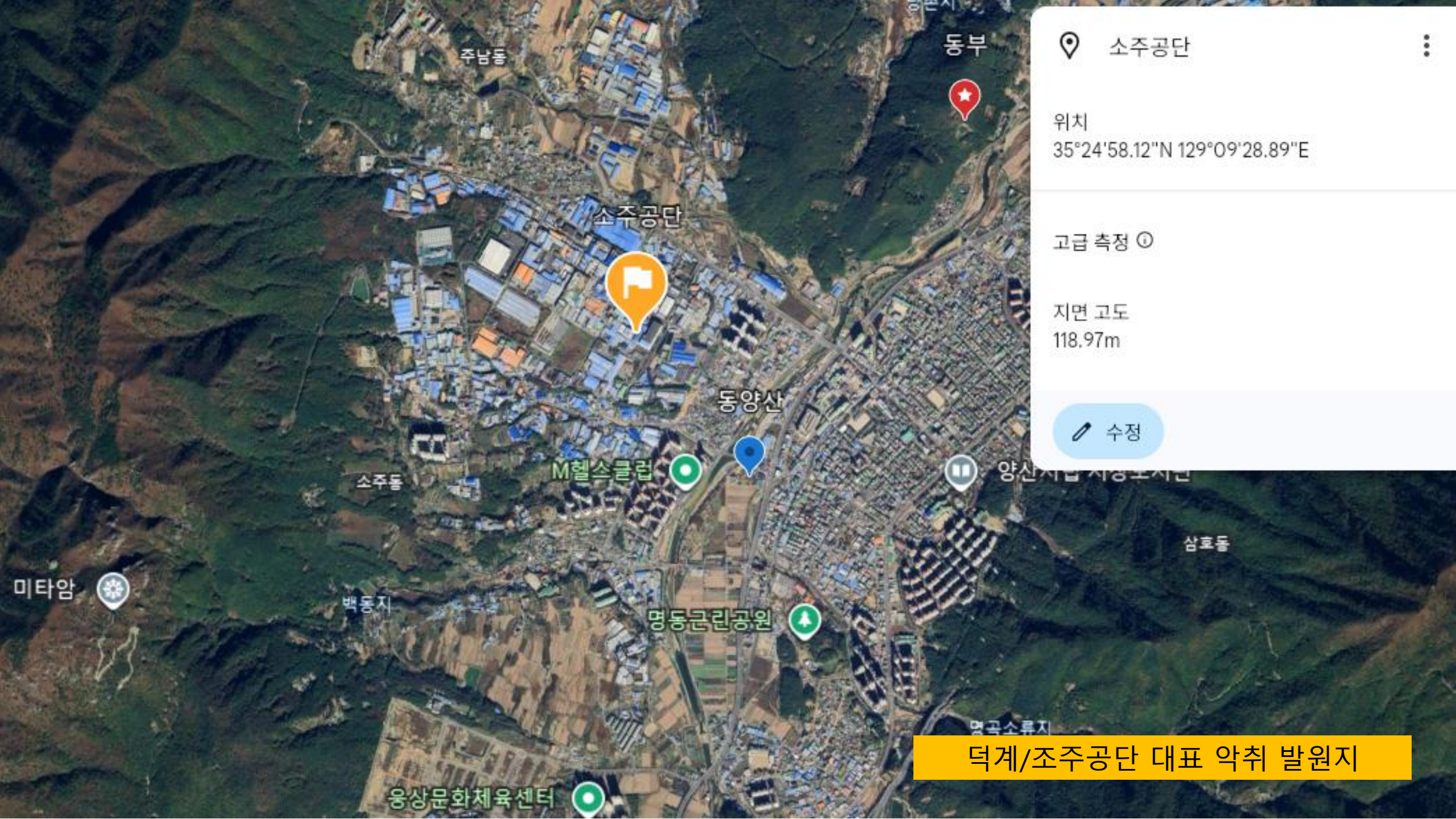
소주공단
위치
35°24'58.12"N 129°09'28.89"E
고급 측정
지면 고도
118.97m
수정
동부
주남동
소주공단
동양산
M헬스클럽
소주동
양산시립 시청소재지
삼호동
미타암
백동지
명동근린공원
명곡소류지
웅상문화체육센터
덕계/조주공단 대표 악취 발원지